CARTOGRAFIÁ PROYECTO TERRITORIO COMUNIDAD XOCHITLAMAPAN.

Importante, las áreas con subdivisiones han sido del consenso de establecer las zonas de custodia de los miembros, entendiéndose no como una lotificación o similar, sino como zonas para nuestras actividades proyectadas en nuestra proyección según planteamientos en nuestros análisis ambientales de 2024 hasta la fecha a diciembre 2025. ***Este documento es estrictamente para miembros queda prohibido compartirlo con externos al proyecto para usos fuera de los deseos comunales. 2025**

ÁREAS DE CONSERVACIÓN PRIVADA COMUNITARIA TOTAL EN VERDE HIERBA.

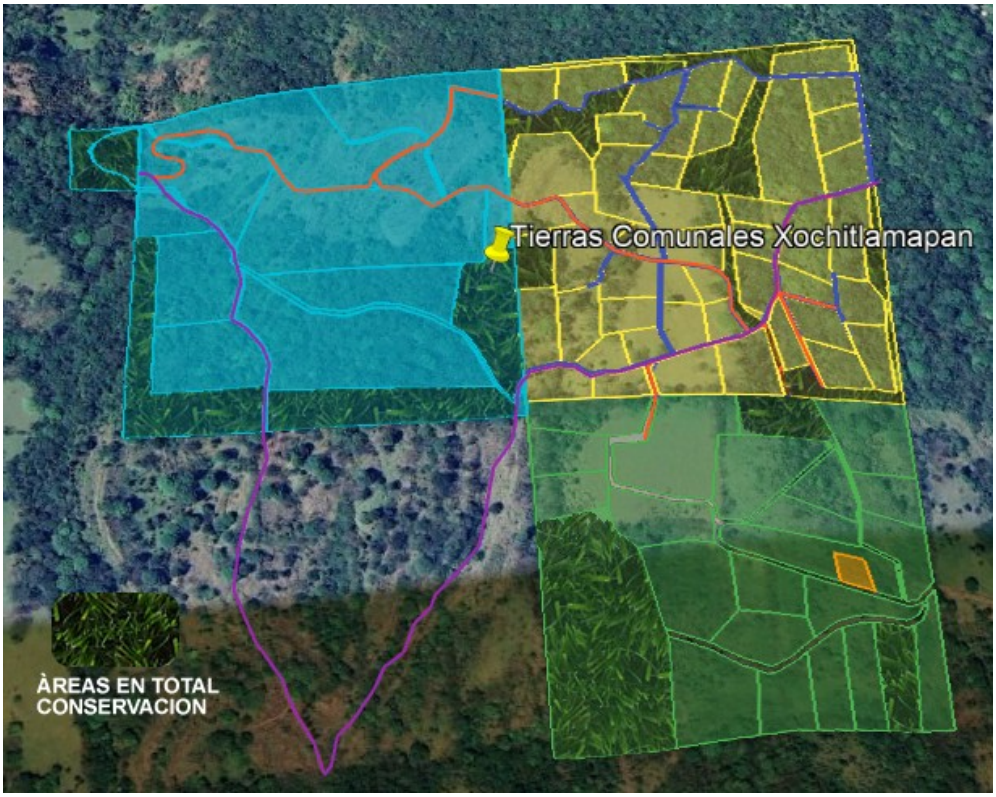

FLUJOS DE AGUA PROYECTO PARA ABASTECIMIENTO, RIEGO Y USO HUMANO.

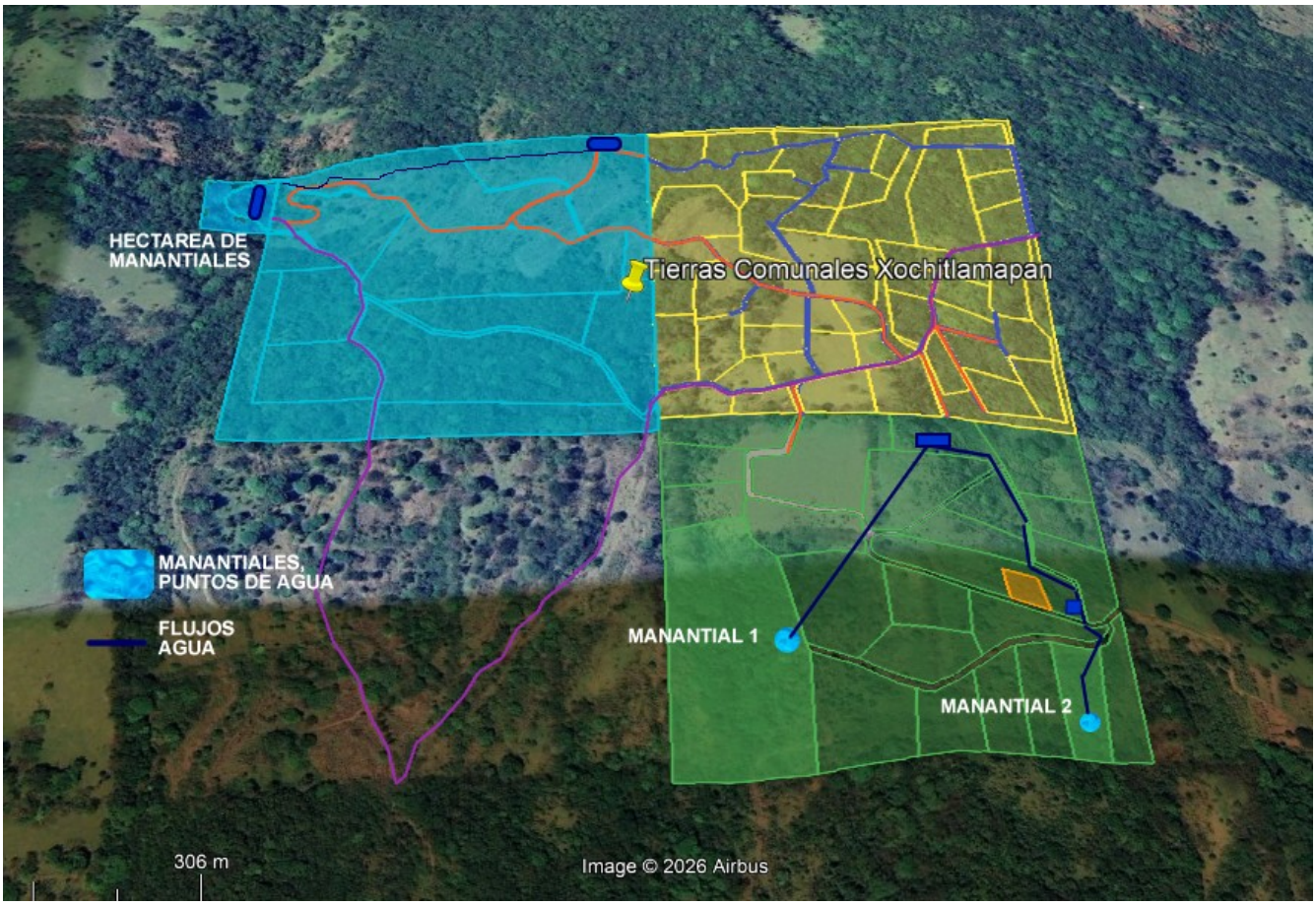

Bombas ariete en Manantial 1 y Manantial 2.
Tanque Reservorio Gigante en la cima entre Fase 2 y 3 para direccionar agua a Fase 2 y 3.

Existen mapas topográficos de Fase 1 y 2 y Pre topografico de Fase 3.

Total territorio unificado.

FASE 1

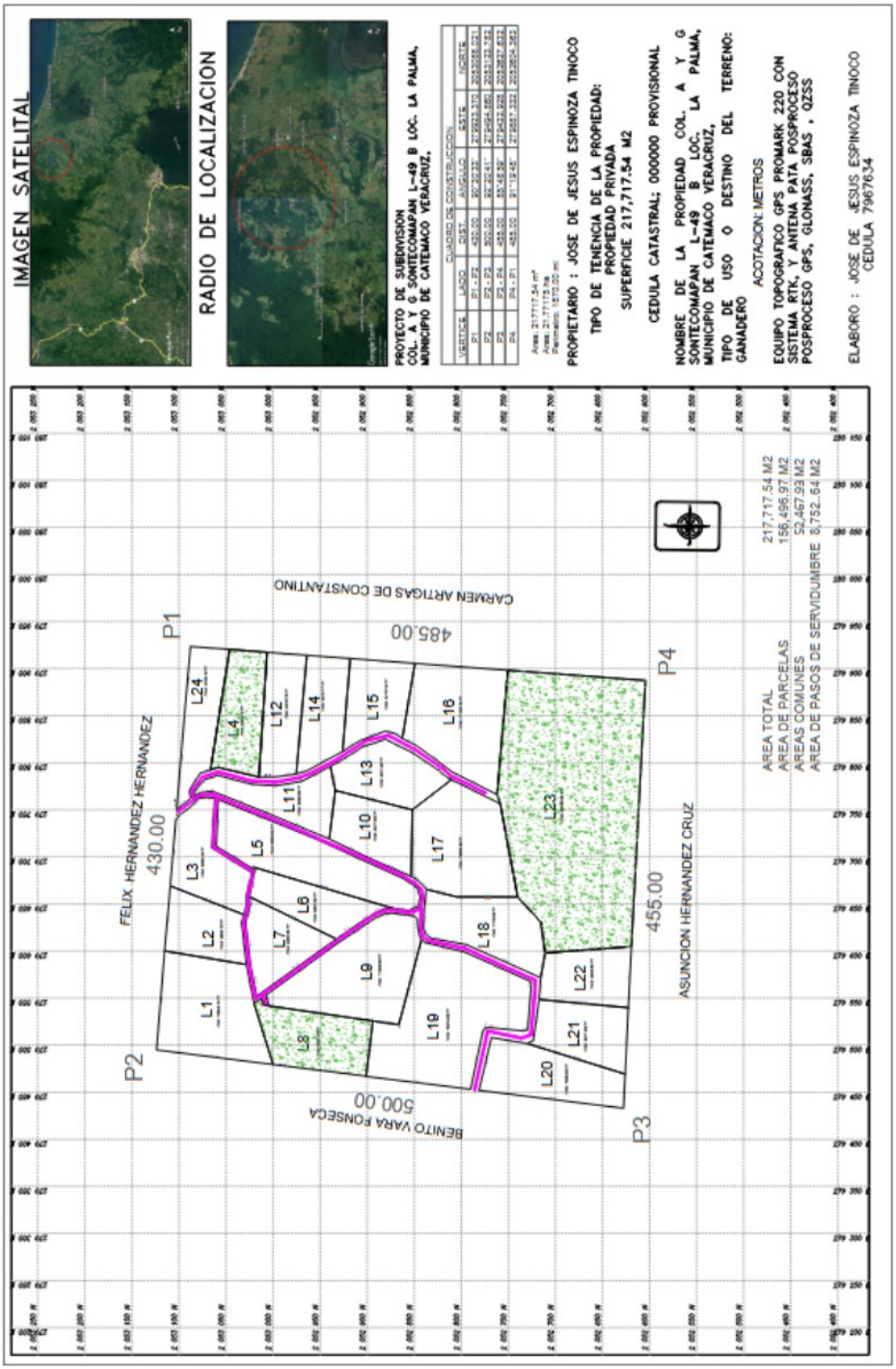
IMAGEN SATELITAL
RADIO DE LOCALIZACION
PROYECTO DE SUBDIVISION
COL. A Y G SONTECOMAPAN L-49 B LOC. LA PALMA,
MUNICIPIO DE CATEMACO VERACRUZ,
CUADRO DE CONSTRUCCION
VERTICE | LADO | DIST. | ANGULO | ESTE | NORTE
P1 | P1 - P2 | 430.00 | 90°30'23" | 279923.310 | 2053088.021
P2 | P2 - P3 | 500.00 | 88°30'41" | 279584.880 | 2053129.324
P3 | P3 - P4 | 455.00 | 88°46'56" | 279432.608 | 2053627.623
P4 | P4 - P1 | 485.00 | 91°19'45" | 279887.332 | 2053604.383
Area: 217717.54 m²
Area: 21.77175 ha
Perimetro: 1870.00 m
PROPIETARIO : JOSE DE JESUS ESPINOZA TINOCO
TIPO DE TENENCIA DE LA PROPIEDAD:
PROPIEDAD PRIVADA
SUPERFICIE 217,717.54 M2
CEDULA CATASTRAL; 000000 PROVISIONAL
NOMBRE DE LA PROPIEDAD COL. A Y G
SONTECOMAPAN L-49 B LOC. LA PALMA,
MUNICIPIO DE CATEMACO VERACRUZ,
TIPO DE USO O DESTINO DEL TERRENO:
GANADERO
ACOTACION: METROS
EQUIPO TOPOGRAFICO GPS PROMARK 220 CON
SISTEMA RTK, Y ANTENA PATA POSPROCESO
POSPROCESO GPS, GLONASS, SBAS , QZSS
ELABORO : JOSE DE JESUS ESPINOZA TINOCO
CEDULA 7967634
CARMEN ARTIGAS DE CONSTANTINO
485.00
P1
P4
FELIX HERNANDEZ HERNANDEZ
430.00
P2
P3
455.00
ASUNCION HERNANDEZ CRUZ
BENITO VARA FONSECA
500.00
L1
L2
L3
L4
L5
L6
L7
L8
L9
L10
L11
L12
L13
L14
L15
L16
L17
L18
L19
L20
L21
L22
L23
L24
AREA TOTAL 217,717.54 M2
AREA DE PARCELAS 156,496.97 M2
AREAS COMUNES 52,467.93 M2
AREA DE PASOS DE SERVIDUMBRE 8,752.64 M2
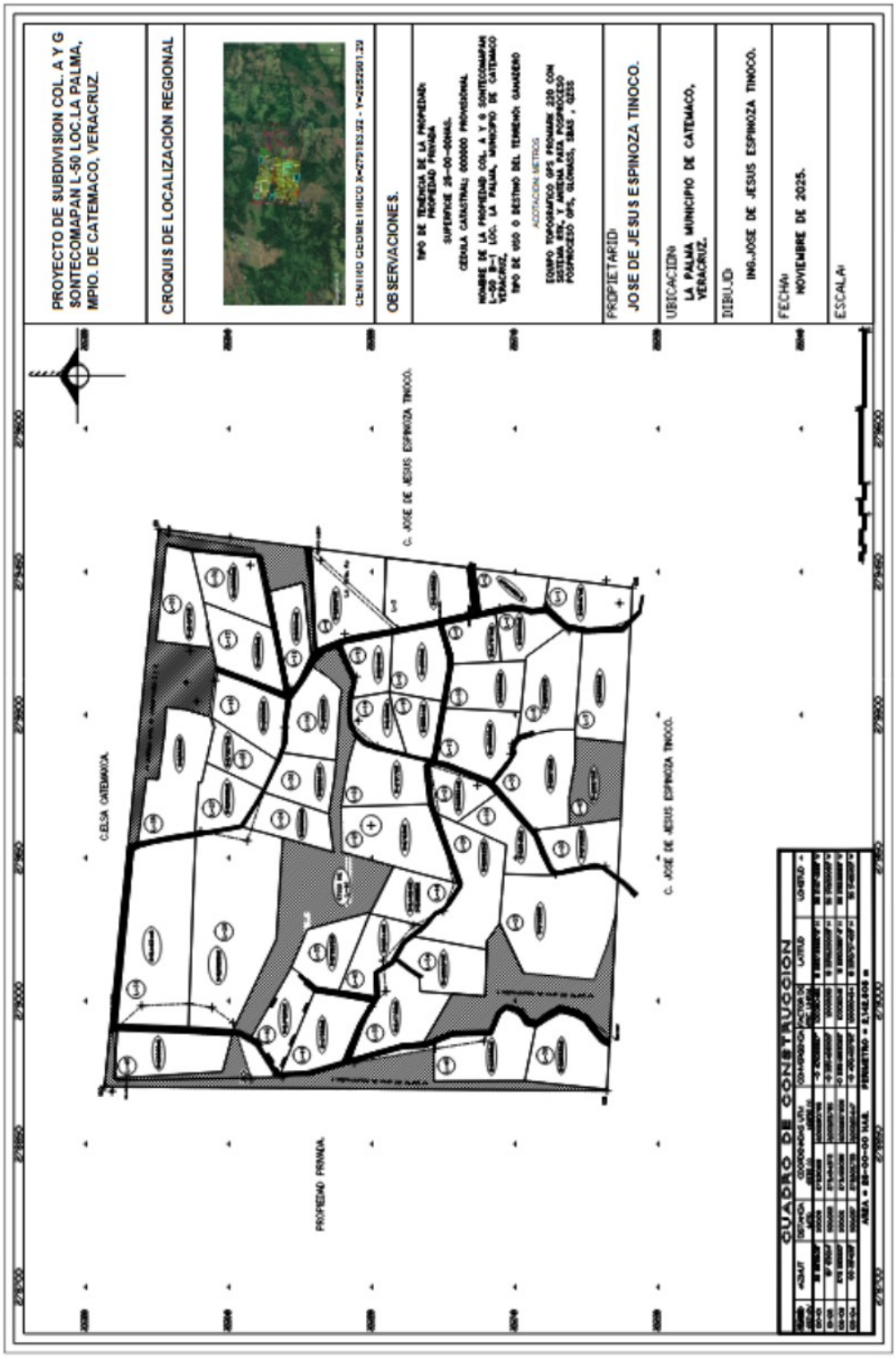
FASE 2
(PREVIO)